ОСОБЕННОСТИ НАЦИОНАЛЬНОГО «О...»

Часть первая – маркированная трасса

Во Всероссийском реестре видов спорта (ВРВС) в разделе «спортивное ориентирование» содержится целых 26 дисциплин, в том числе 12 кроссовых, 10 лыжных и 4 велосипедных.

На международных соревнованиях ИОФ используется гораздо меньшее их количество, особенно в лыжных и кроссовых видах программы. Некоторые используемые у нас дисциплины практически неизвестны (или мало популярны) в других странах. Мы предлагаем вашему вниманию обзор тех видов программы, которые, по сути, являются нашим национальным изобретением и достоянием. И начнем мы, естественно, с нашей родной «маркировки».

Ориентирование на маркированной трассе обязано своим появлением двум обстоятельствам. И первое, что приходит на ум, желание продолжать соревноваться зимой, когда передвигаться по лесу на ногах в некоторых регионах практически невозможно. В чем же дело? Все встаем на лыжи!!! Но как быть со следами? Передвигаться по снежной целине очень трудно, особенно идущему впереди. А сзади становится заметно легче. Да и думать особенно не надо. Лыжня (или просто след), она хоть и кривая, но вывезет! Так что провести соревнования в равных для всех условиях не получается. Тогда-то и была изобретена маркированная трасса, то есть, по сути, «навигация наоборот».

Фактор снежного покрова оказался не единственным обстоятельством в пользу появления такого «развлечения».

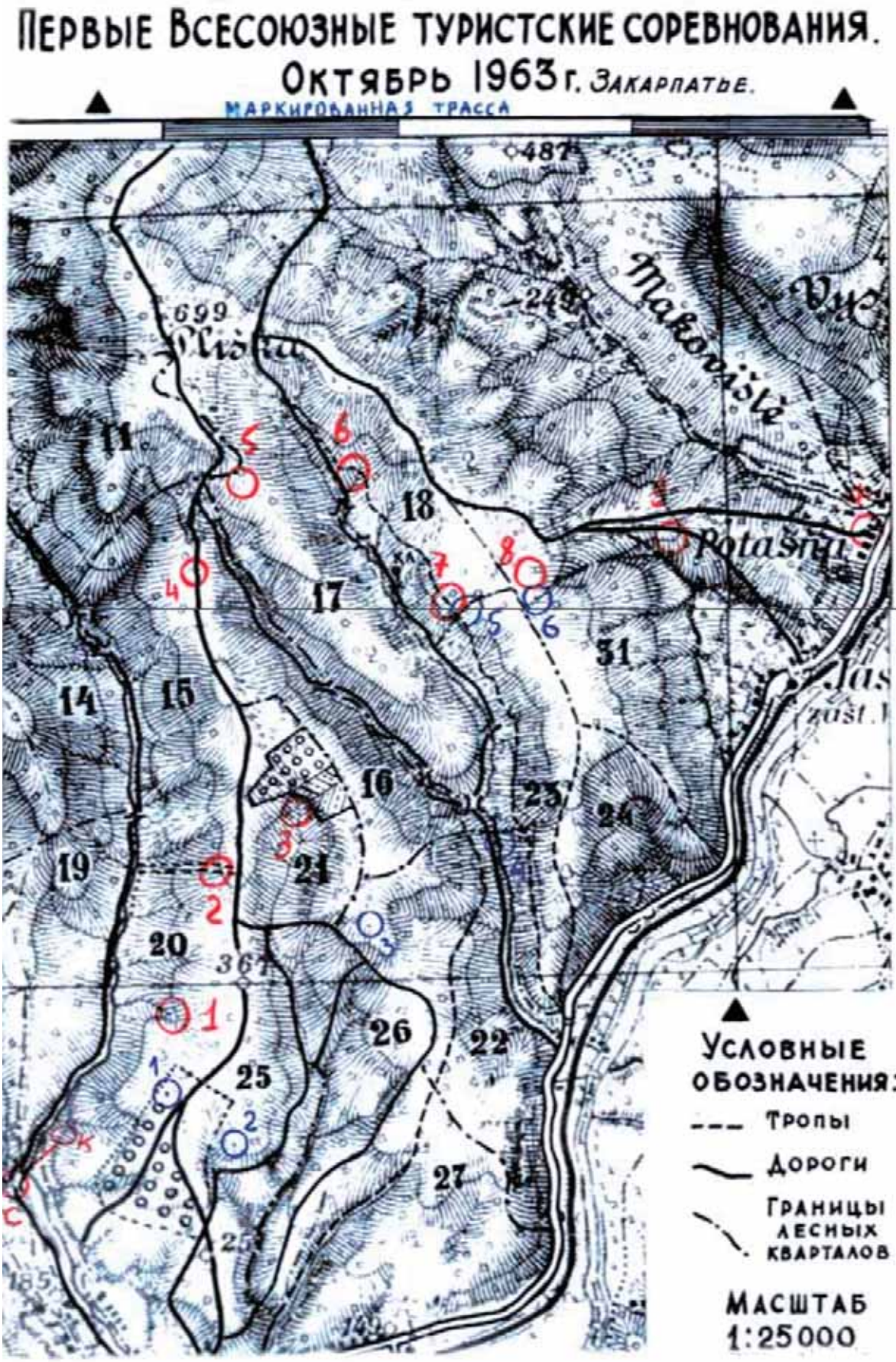

Рис. 1. Карта Всероссийских соревнований в Ужгороде. Масштаб 1:25 000, составлена на основе старой венгерской топографической карты масштаба 1:50 000. Горизонталей нет, рельеф отображен штриховкой. Красные КП на мужской дистанции, синие – на женской.

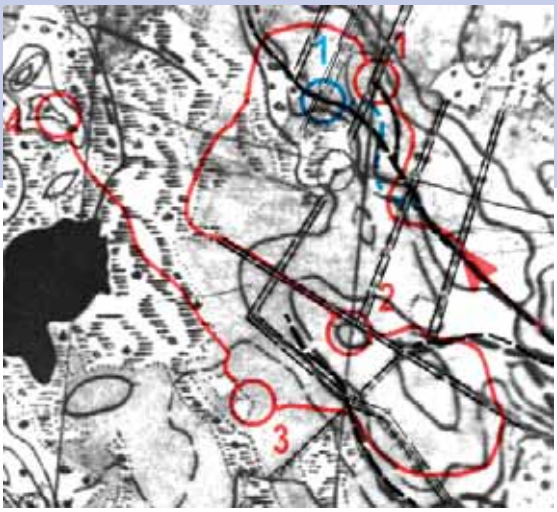

Рис. 2. «S-петля» на подходе к КП 1. Постановка КП на формах рельефа без точечной фиксации положения КП (2 и 4). Постановка КП 3 с высокой точностью на границе растительности (угол поляны).

Рис. 3. Чемпионат Ленинграда на маркированной трассе (февраль 1973 года).

Когда в 1963 году в Ужгороде состоялись первые Всероссийские соревнования, летние, а не зимние, ориентирование на маркированной трассе стало первым видом программы, в котором были разыграны медали. А вот на дистанцию заданного направления на следующий день участники выходили уже парами. Руководство Центрального Совета по туризму и экскурсиям (при ВЦСПС, а не при Спорткомитете СССР) решило, что выпускать людей в лес поодиночке небезопасно. Мало ли еще заблудятся, потеряются, а местность горная, суровая, да еще и венгерская граница неподалеку. А по разметочке они придут на финиш, никуда не денутся.

И вот 12 октября 1963 года с интервалом 1 минута на дистанцию отправились 145 женщин и 151 мужчина. Первыми победителями Всероссийских соревнований (по сути, чемпионами СССР) стали Л. Штаролите из Литовской ССР и М. Аруя из Эстонской ССР. Результат (как это было принято тогда и сохраняется с тех пор, за исключением самой системы начисления штрафа, которая в дальнейшем постоянно подвергалась пересмотру) определялся по сумме времени прохождения дистанции и начисленного штрафного времени. Оно (штрафное время или попросту «штраф») определялось в зависимости от расстояния между проколом на карте участника и истинным положением КП. Первые три миллиметра не штрафовались, а далее штраф определялся по системе: одна минута за каждый миллиметр отклонения. В итоге победитель у мужчин преодолел трассу длиной около 12 км в горной местности с 9 КП за 1 час 31 минуту и 26 секунд. Но к этому времени было добавлено 54 минуты штрафного времени. Несмотря на столь значительный штраф, он стал победителем, ведь средний штраф первой десятки у мужчин составил 59 минут (что дало в среднем 8,3 минуты на один КП). Наибольшую «точность» показал ленинградский ориентировщик А. Котов (40 минут), что принесло ему итоговое второе место. А вот быстрейший на дистанции Р. Славиньш из Латвийской ССР заработал 84 минуты штрафа и остался лишь пятым. Победительница женских соревнований преодолела дистанцию длиной 7 км с 7 КП за 1 час 19 минут и 37 секунд, добавив к этому 14 минут штрафа. Женщины справились с технической частью лучше, чем мужчины. У них средний штраф первой десятки составил 17,8 минут (это всего лишь 2,5 минуты на один КП), при этом две участницы обошлись без штрафа. Правда, медалей им это не принесло.

Три миллиметра «льготы» были абсолютно необходимы по следующим причинам. Во-первых, даже сам начальник дистанции не мог с абсолютной точностью определить истинное положение КП на карте, уж такого качества картографические материалы использовались в те годы. Во-вторых, само положение КП на карте не всегда было точкой (в отличие, например, от пересечения линейных ориентиров). Если КП ставился по рельефу, то его «точка» превращалась в некую «область». В-третьих, участнику надо было дать право на небольшую ошибку. Правда, некоторые пользовались этим обстоятельством очень искусно, делая прокол между двумя возможными параллельными ситуациями, что позволяло либо избежать штрафа совсем, либо свести его к минимуму. Особых разносолов начальники дистанции предложить не могли, читать на тех картах было особо нечего. Поэтому они изобретали специальные приемы и «приемчики». Один из них, так называемая «S-петля», продемонстрирован на рис. 2. Красная линия – реальная трасса, синяя линия – возможная версия участника, ведущая в параллельную ситуацию. Контрольные пункты привязывались к формам рельефа (с погрешностью, поскольку рельеф изображался весьма условно и со значительной генерализацией), а также к границам растительности, реже к линейным ориентирам (в точках развилок, пересечений или хорошо выраженных изгибов).

Приводим фрагмент карты Чемпионата Ленинграда на маркированной трассе 1973 года (мужская дистанция, 13 км 13 КП). При безлимитной системе штрафа плотность один КП на километр трассы была вполне достаточной для того, чтобы заставить участника качественно ориентироваться на протяжении всей трассы. Специально подготовленная спортивная карта давала возможность постановки КП в зонах сложного рельефа.

В дальнейшем качество карт улучшилось, появилась цветная типографская печать. Для прокладки маркированных трасс районы стали выбирать с особой тщательностью. Во-первых, они должны были быть достаточно проходи-

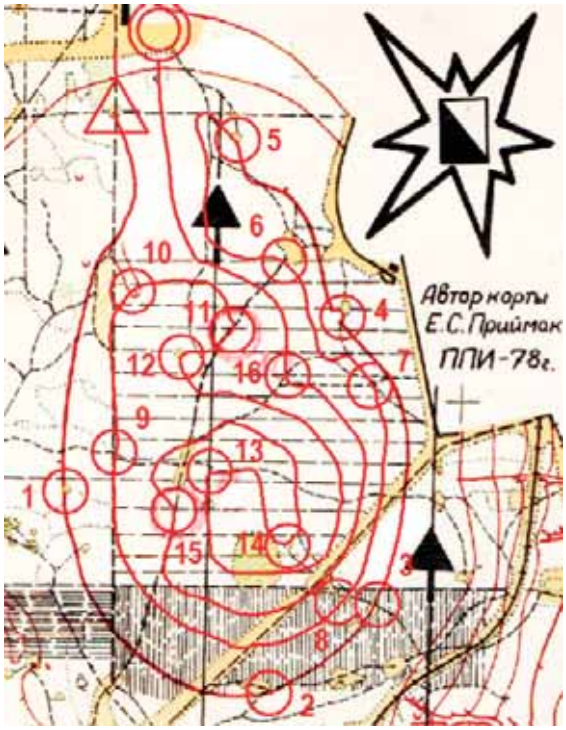

Рис. 4. Вертушка Приймака (1978).

Рис. 5. Ленинградская вертушка (1983).

мыми, чтобы не пришлось прорубаться сквозь заросли и буреломы. Во-вторых, насыщенными различными ориентирами, в первую очередь формами рельефа с высокой степенью детализации. Но даже в относительно «бедных» районах применялись особые приемы, позволявшие ставить перед участниками довольно сложные задачи. Возможно не все они были на сто процентов корректными, но по-своему весьма интересными. Один из таких приемов получил негласное название «вертушка (или улитка) Примака», по имени его изобретателя – выдающегося пермского специалиста: тренера, судьи и картографа Е.С. Примака. Что представляет собой этот прием, можно увидеть на рис. 4. А вот как описывал его безвременно и трагически ушедший из жизни мой хороший друг, спортсмен и тренер Анатолий Чертовицкий, светлая ему память:

«Приезжаем на старт. Лес пермский, прозрачный, видимость до 100 метров и более. Смотрим в сторону трассы – все фишки видно. Ошалевший народ едет по трассе, при этом слева и справа по параллельным лыжням несутся навстречу с выпученными глазами участники. Каждую призму ты видишь раз по пять-шесть, но совершенно невозможно предвидеть, когда она тебе попадется на трассе…»

Автору этих строк не довелось повертеться самому в «чертовом колесе», но эту идею он использовал неоднократно, включая подобные участки в свои «маркировки» на ленинградской земле. Один из таких фрагментов вы можете увидеть на рис. 5.

Небольшое, но важное замечание. Обе приведенные здесь «вертушки» виртуальные. Карты настоящей вертушки Примака в моей коллекции просто нет, пришлось изобразить нечто подобное, соответствующее описанию А. Чертовицкого. А ленинградская вертушка использовалась на маркировке в этом районе (так называемая Малиновая гора), но несколько в иной части карты.

Система отметки (фиксации проколов) видоизменялась неоднократно. В начале славного пути для этого использовались цветные карандаши, которые вывешивали на КП. Участник был обязан сделать прокол и обвести его цветным карандашом не далее, чем на следующем КП. Поэтому на первом КП карандашей не было, зато после последнего КП оборудовался специальный «рубеж отметки последнего КП», без призмы, но с карандашами. Тут же нашлись «мудрецы», которые делали кружок диаметром в пару сантиметров и более, для того чтобы иметь возможность сделать прокол попозже, в надежде что-то додумать, либо, что более вероятно, спросить, где находится КП, у догнавшего его товарища по команде или даже у соперника. Для борьбы с этим диаметр кружка ограничили несколькими миллиметрами, а затем перешли к отметке «крестом», при этом расстояние от прокола до центра креста не должно было превышать 3 мм. Но и это препятствие «умные головы» научились обходить весьма оригинальным путем. Они просто обкусывали грифели и на рубеже последнего КП выплевывали их на свой планшет. Важно было не перепутать, какой карандаш был на котором КП. Естественно, «обкусыванию» подлежали только карандаши на тех КП, положение которых вызывало у участника сомнение. Тем же, кто бежал позади, приходилось грызть карандаши зубами, чтобы добраться до грифеля. Но инженерная мысль настоящего ориентировщика никогда не стоит на месте. Наша отечественная маркировка дала жизнь такому изобретению как «штемпельный компостер-игла», оставлявшему на карте не только прокол, пусть и довольно слабый, но находящийся строго по центру того кружка, который отпечатывался на карте. Номер КП отпечатывался внутри кружка. Штемпельная подушка прикреплялась к дереву рядом с КП. Вторым изобретением стала машинка для нанесения мишеней на обратную сторону карты, которая потом закрывалась непрозрачной бумагой.

Улучшение качества карт, а также выработка и соблюдение принципов прокладки трассы и постановки КП привело к тому, что среднее время штрафа на соревнованиях сократилось в значительной мере. Клуб «зеро» на каждых соревнованиях насчитывал уже не двух-трех, а не один десяток человек. При безлимитном штрафе допускать небрежность или невнимательность в ориентировании было себе дороже. Один КП мог лишить спортсмена всех шансов на мало-мальски приличный результат. Тем не менее, у этой системы штрафа находились противники, особенно те, кто хорошо владея лыжами, не смогли показать достойный результат из-за большой ошибки на одном-двух КП. Первым шагом стало ограничение максимального штрафа 10 минутами. Затем было принято еще более радикальное решение. Штраф назначался дискретно: ноль до 2 мм, одна минута до 4 мм, две – до 6 мм, далее 3 минуты. Затем и эту систему сократили, отбросив «последнюю ступень». Максимальный штраф на одном КП стал составлять всего 2 минуты. Но условные «лыжники» рано радовались. Было введено правило 50%.

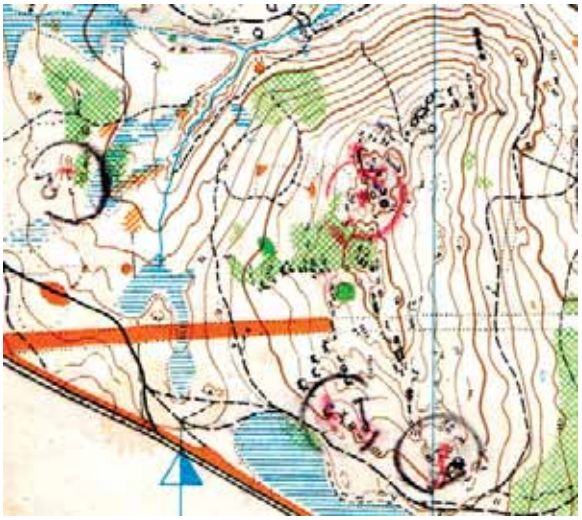

Рис. 6. Отпечатки отметки штемпельным компостером-иглой (Чебаркуль, Первенство ВС СССР, 1980 г.)

То есть, если спортсмен получал максимальный штраф (2 минуты) на более чем половине КП, его результат аннулировался с формулировкой «снят за техническую неподготовленность». Интересно отметить, что каждое послабление в начислении штрафа приводило не к уменьшению среднего штрафа первой десятки итогового протокола, а к его увеличению. Что, впрочем, не удивительно, ведь расплата за серьезную ошибку заметно уменьшилась, риск стал более оправданным и, соответственно, более востребованным. Скорости возросли, а требования к качеству ориентирования упали.

Все системы штрафа, сменявшие друг друга со все увеличивающейся частотой, оставались, тем не менее, довольно сложными и противоречивыми до тех пор, пока мы не пришли к современной, максимально упрощенной системе по типу ЕГЭ: «угадал/не угадал», по существу убившей всю прелесть нашей родной «маркировки». Но это уже совсем другая история.

Некоторое внимание хотелось бы уделить подготовке трасс в лыжном отношении. В эпоху деревянных лыж трассы прокладывались без использования техники, то есть ногами. В Правилах соревнований по «ориентированию на местности» (так назывался наш вид спорта, пока он находился в системе Совета по туризму) было написано так: «лыжней считается след, по которому прошли перед участниками не менее десяти человек». Нетрудно представить, что представляла собой такая, с позволения сказать, трасса. Впрочем, по ходу соревнований она постепенно улучшалась, и последние участники находились в значительно более выгодных условиях. Отдельные «продвинутые» дистанционщики прокладывали справа и слева небольшой след для палок. Приход студенческой молодежи, а особенно появление «свободных от выполнения производственных обязанностей» спортсменов-военнослужащих, позволили уделять подготовке трасс больше времени и сил. «Трассоукладчик» бригады 5-го СКА Ленинградского военного округа состоял из 8-10 человек. Впереди шел «разведчик». Он смотрел по карте, в какую сторону надо вести трассу, и выбирал мало-мальски пригодный для нее коридор между деревьями. Это должен был быть опытный ориентировщик, зачастую сам автор карты. Он имел право на ошибку, поэтому вся остальная бригада шла на расстоянии 100-200 м от него, чтобы он имел возможность исправлять свои навигационные погрешности. Остальную часть бригады возглавлял «выпрямитель», который сглаживал углы и повороты, подчищая работу «разведчика». Слева и справа от него шли два «чистильщика» с топорами и секирами. Они обрубали ветки, чистили трассу от упавших стволов, подлеска и мелких прутиков, по мере надобности вырубали попадавшиеся под снегом пеньки. Далее шли «топтуны» (не путать с агентами внешнего наблюдения правоохранительных органов), от одного до четырех человек, в зависимости от глубины и плотности снега. Как правило, первые двое ставили лыжи под углом к трассе (крест-накрест относительно друг друга), остальные (один или два) топтали снег строго поперек будущей лыжни. При необходимости один или два человека уплотняли дорожки под палки слева и справа от основной лыжни, которую прокладывал «челнок-прокладчик», успевавший проложить классическую параллельную лыжню и прокатиться по ней вперед-назад не менее десяти раз. Такой «трассоукладчик» передвигался по лесу со скоростью от 0,5 до 1 км/час, в зависимости от густоты растительности и глубины снежного покрова. Трассу эстафеты Чемпионата Ленинграда зимой 1084 года, протяженностью не менее 10 км, эта бригада подготовила всего за 2 полных световых дня. При таком способе прокладки трассы нельзя было оставлять ни одного не доведенного до идеала участка, особенно в оттепель, поскольку на следующий день понижение температуры могло превратить недоделанную трассу в нечто неудобоваримое, а главное, не подлежащее исправлению. Конечно сейчас, в эпоху механизированной прокладки трасс, такая работа выглядит архаичной, но на неровной бугристой поверхности результат ручной, точнее «ножной» работы выглядел порой предпочтительнее «машинной».

Разметка трассы почти что не требовалась. Такой след настолько отличался от всего того, что можно встретить в лесу, что сбиться с него было практически невозможно. Тем не менее, время от времени для разметки трасс использовались лыжные флажки, либо окрашенные разноцветной гуашью перфокарты (те, кто родился в XXI веке, пожалуй, и не знают, что это такое). В дальнейшем перешли на листы цветной бумаги, прикрепляемые к стволам деревьев степлером. Те, кто следует принципам защиты природы, степлеры с металлическими скрепками не используют, а просто наносят на стволы пятна краски из баллончиков.

Конечно, сейчас нет смысла возвращаться к старой, «ножной» системе

Рис. 7. Схема работы «трассоукладочной» бригады.

подготовки трассы, тем более, с учетом того, что все ориентировщики давно уже перешли на коньковые лыжи. Но навык прокладки качественной лыжни может пригодиться во время лыжного сбора, если в распоряжении тренера по какой-то причине не оказалось снегохода типа «Буран».

Переход к новой, современной системе проведения соревнований на маркированной трассе был абсолютно неизбежен. Основные причины таковы:

- Обсчет штрафа по линейке с делениями ненадежен и трудоемок. Порой результаты соревнований оставались неизвестными до следующего утра, при этом вся бригада дистанции вместе с секретарями обсчитывала штрафное время целую ночь. Нанесение мишеней на обратную сторону карты решало проблему лишь частично.

- Планшет для проколов и отметок на карте должен быть открытым, а современные планшеты оборудованы плотной прозрачной пленкой для защиты карты от влаги, механических повреждений и, главное, от потери карты на ходу.

Современные требования к спортивной карте таковы, что она, карта то есть, должна отображать состояние местности на данный момент, а не то, как она выглядела в бесснежный период. Следовательно, основная лыжня трассы должна быть обозначена на карте, что упрощает ориентирование до почти что неприличного предела. Поэтому единственной абсолютно справедливой системой проведения маркированной трассы является использование карты с нанесенной на нее сеткой лыжней, подготовленных для других видов программы.

Тем не менее, ветераны ориентирования хорошо помнят те самые легендарные маркировки, когда на одном КП можно было получить до пары часов штрафа.

А. ШИРИНЯН
(г. Санкт-Петербург)